自然资源部南海预报减灾中心

海洋环境月报

时间：　2025 年 08 月 26 日

编号：　天文大潮 202509　　签发：　许炜铭

2025 年 9 月华南沿岸天文大潮月报

9 月，广西沿岸天文大潮期间潮位较高，其中涠洲站将于 15-16 日出现超过当地蓝色警戒潮位的高潮位，请做好防范工作。

粤东沿岸天文大潮将出现在 7-12 日和 24-27 日，在当地蓝色警戒潮位 31 厘米以下，其中饶平站潮位较高；大湾区沿岸天文大潮将出现在 7-14 日、19-21 日和 26-29 日，在当地蓝色警戒潮位 9 厘米以下，其中黄埔站潮位较高；粤西沿岸天文大潮将出现在 7-9 日和 21-26 日，在当地蓝色警戒潮位 4 厘米以下，其中水东站潮位较高。

海南沿岸天文大潮将出现在 5-8 日、14-18 日和 28-30 日，在当地蓝色警戒潮位 7 厘米以下，其中海口站潮位较高。

广西沿岸天文大潮将出现在 5-8 日、14-18 日和 29-30 日，其中涠洲站将于 15-16 日出现超过当地蓝色警戒潮位的高潮位。

区域	粤东	大湾区	粤西	海南	广西
代表站	饶平站	黄埔站	水东站	海口站	涠洲站
月最高潮位（cm）	104	176	181	179	448
最高潮位出现时间	10 日 15:00、11 日 15:48 和 24 日 14:46	08 日 12:12	08 日 10:45	15 日 11:44	15 日 10:55
警戒潮位（cm）	135（蓝）	185（蓝）	185（蓝）	186（蓝）	440（蓝）

注：1. 广东省岸段潮位基面为珠江基面，海南岛、广西区岸段潮位基面为 1985 高程基准，涠洲站潮位基面为当地水尺；

2. 潮位值（1985 国家高程基准）= 潮位值（珠江基面）+74.4cm；

3. 1985 高程基准是采用青岛水准原点和根据由青岛验潮站 1952 年到 1979 年的验潮数据确定的黄海平均海水面所定义的高程基准。其水准原点起算高程为 72.260m。

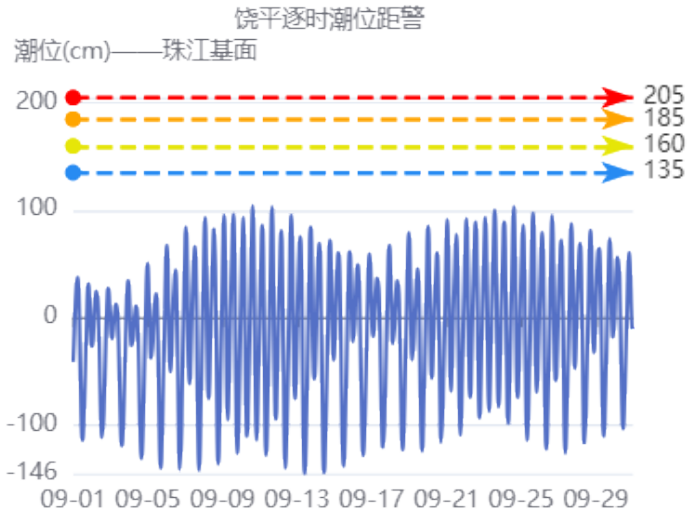
饶平逐时潮位距警
潮位(cm)——珠江基面
200
100
0
-100
-146
205
185
160
135
09-01 09-05 09-09 09-13 09-17 09-21 09-25 09-29

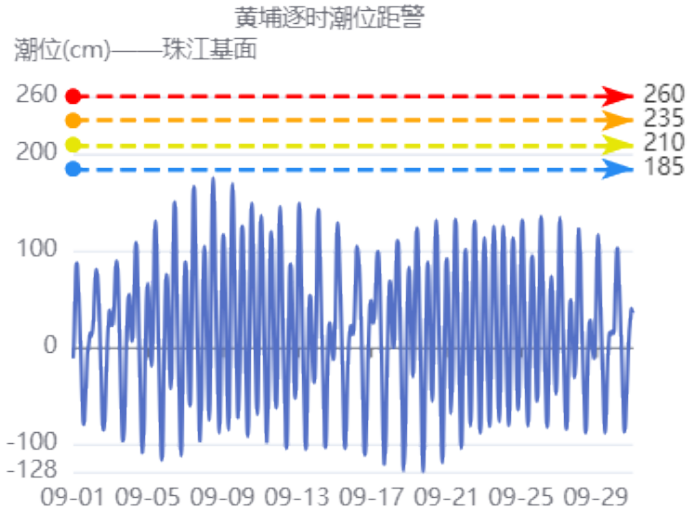
黄埔逐时潮位距警
潮位(cm)——珠江基面
260
200
100
0
-100
-128
260
235
210
185
09-01 09-05 09-09 09-13 09-17 09-21 09-25 09-29

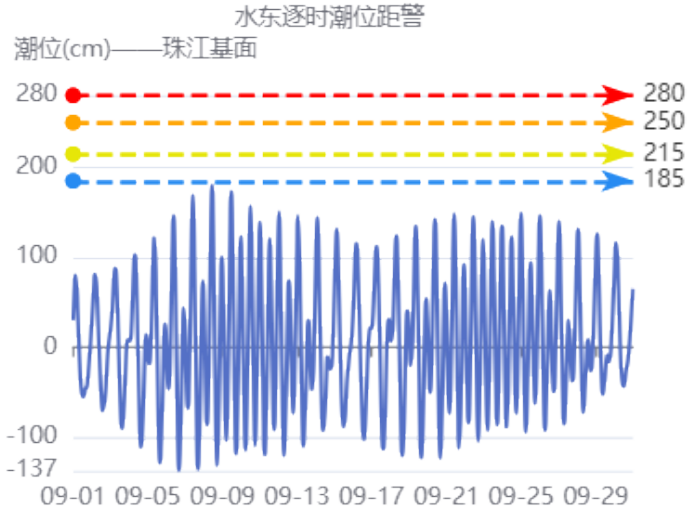
水东逐时潮位距警
潮位(cm)——珠江基面
280
200
100
0
-100
-137
280
250
215
185
09-01 09-05 09-09 09-13 09-17 09-21 09-25 09-29

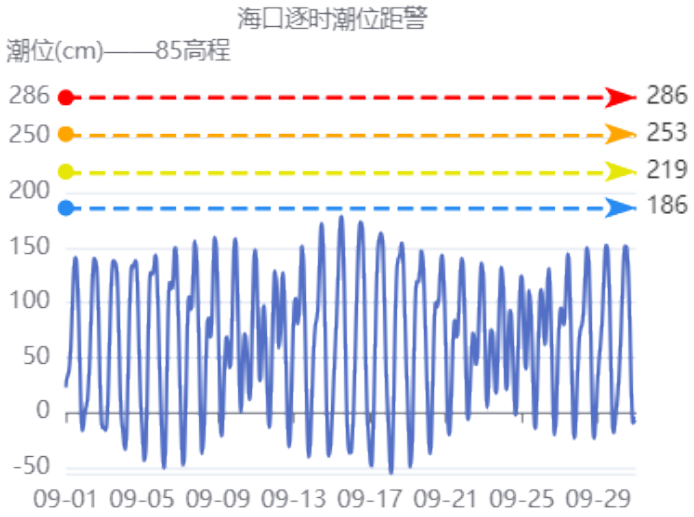

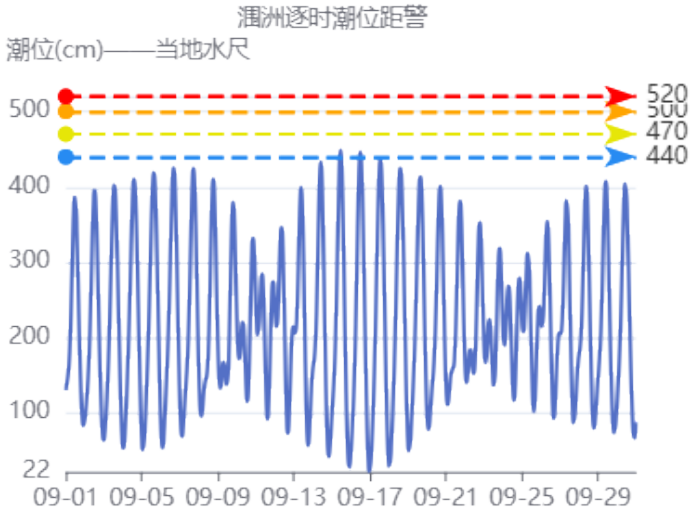

发往：

联系人：李希茜　　**电话：**84220068　　**网址：**http://www.hyyb.org